7.

C O P I A D E A C T A:

CONC... PAR... A P... ...AL DE GRAU ...O

El que suscribe,el Alcalde del Distrito de Petaypampa,Provincia de Grau Departamento de Apurimac.- - - -

/° 00001

ción : INSCRIPCION DE PLANO DE TRAZADO Y LOTIZACION

IETARIO - TITULAR : COFOPRI

a del Predio : 7,946.64 M2

so del Predio : AREA DESTINADA A EDUCACION

Medidas y Colindancias

LINDEROS	MEDIDAS	COLINDANCIA
FRENTE	119.07 ML	AV. CENTENARIO
DERECHA		CARRETERA A C.C. SANTA ROSA
1	.33	CARRETERA A C.C. SANTA ROSA
2	23.48	
3	11.1	
4	39.56	
5	2.48	
6	15.05	
IZQUIERDA		LOTE 2, C.C. SANTA ROSA
1	17.34	LOTE 2, C.C. SANTA ROSA
2	10.47	
3	24.53	
4	19.24	
5	15.17	
6	9.04	
7	10.32	
8	24.46	
9	12.92	
10	8.86	
FONDO		C.C. SANTA ROSA, CARRETERA A C.C. SANTA ROSA
1	10.72	C.C. SANTA ROSA, CARRETERA A C.C. SANTA ROSA
2	19.48	
3	22.66	
4	8.74	
5	15.25	
6	14.28	
7	13.73	
8	7.58	

Títulos que dan mérito a la Inscripción

1 **PLANO DE TRAZADO Y LOTIZACION** Nº 046-COFOPRI-2015-OZAPUC SUSCRITO POR ING. JOSE LUIS VASQUEZ LA ROSA JEFE DE LA OFICINA ZONAL DE APURIMAC (ABANCAY)

2 **RES. COFOPRI** Nº 052-2015-COFOPRI/OZAPUC 22/10/2015 SUSCRITO POR ING. JOSE LUIS VASQUEZ LA ROSA JEFE DE LA OFICINA ZONAL DE APURIMAC (ABANCAY)

3 **PLANO PERIMETRICO** Nº 044-COFOPRI-2015-OZAPUC SUSCRITO POR ING. JOSE LUIS VASQUEZ LA ROSA JEFE DE LA OFICINA ZONAL DE APURIMAC (ABANCAY)

4 **INFORME TECNICO CATASTRAL** Nº 1764-2015-ZRN°X/OC-OR-ABANCAY-R 02/11/2015 SUSCRITO POR ESPECIALISTA DE CATASTRO DE LA ZONA REGISTRAL N° X-SEDE CUSCO ARQ. ZORAIDA VALENZUELA CHIRINOS.

5 **OFICIO COFOPRI** Nº 1387-2015-COFOPRI/OZAPUC 22/10/2015 SUSCRITO POR ING. JOSE LUIS VASQUEZ LA ROSA JEFE DE LA OFICINA ZONAL DE APURIMAC (ABANCAY)

Asiento de presentación Nro. 2015 - 00009212 del 22/10/2015 a horas 18:31:16 **Arancel :** S/. 0.00

Recibo(s) 2015-04-00016106

Registrador Público ALZAMORA CANCINO BRENO ULIANOV

Fecha de Inscripción 05/11/2015 **Oficina Registral :** ABANCAY

Superintendencia Nacional de Registros Públicos
Zona Registral N° X Sede Cusco
ABANCAY

Gaby González Palomino
CERTIFICADOR
ZONA REGISTRAL N° X SEDE CUSCO
OFICINA REGISTRAL DE ABANCAY

02-C.- INSCRIPCION DEFINITIVA.- EL MINISTERIO DE EDUCACION- a través del COLEGIO SECUNDARIO DE MENORES DE PATAYPAMPA, representado por el Director de Educación Prof. V. Walter Morales Dongo, ha pasado a ser propietario en forma definitiva del inmueble inscrito preventivamente en èsta partida, en mèrito a lo prescrito por el Art. 7 de la Ley 26512, adjuntándose para el efecto la publicación correspondiente en el Diario Oficial el Peruano, solicitud del Director de Educación de Apurimac y copia de la Escritura Pública de fecha 12 de agosto de 1982 extendida por ante Notario Público Maria N. de Molina.- Presentación Diario: 08-11-99.-TITULO:4233.-ASIENTO:096.-RECIBO:0353.-HORA:12:09.- LEG PIN 074.-DERECHOS:S/. 00.00.-ABANCAY, 10 DE NOVIEMBRE DE 1999.

Abg. OPBLA JORIAN GAMARRA
REGISTRADORA PUBLICA

Copia Certificada
Sin Inscripcion al Dorso
No hay Títulos Suspendidos y/o Pendientes de Inscripción
A Horas : 8:00 AM

Zonia Nacional de Registros Públicos
Zona Registral N° X Sede Cusco

Dahyl Gutiérrez Palomino
CERTIFICADOR
ZONA REGISTRAL N° X SEDE CUSCO
OFICINA REGISTRAL DE ABANCAY

ID : 5282922 Recibo Nº 2016-678-7265 CERTI. LITERAL - PREDIOS Partida Nº 05002554

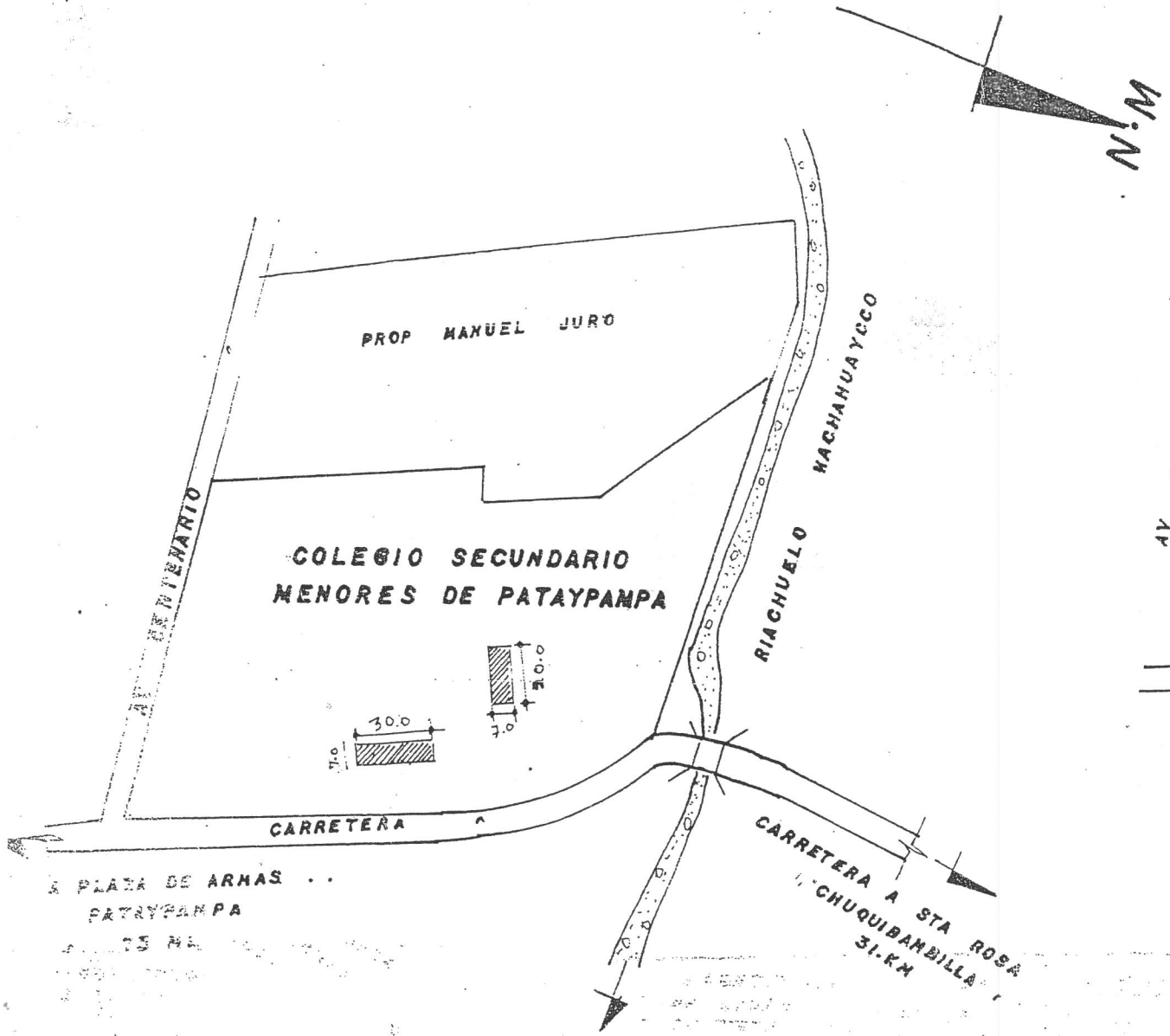

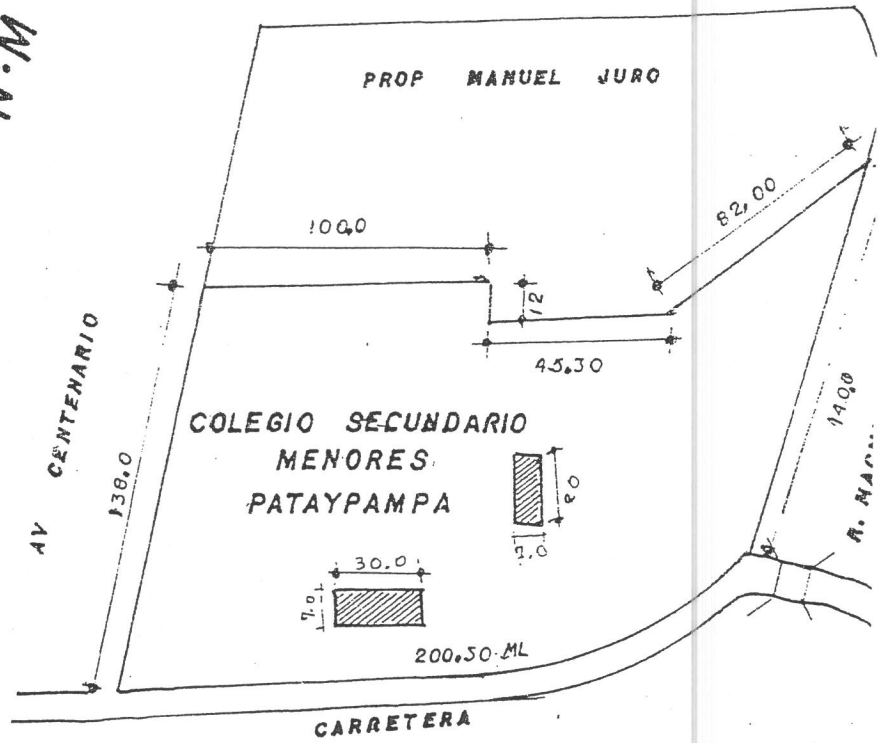

C.S. MENORES PATAYPAMPA			
PROP	MINISTERIO DE EDUCACION		
PLANO	UBICACION Y PERIMETRICO		
AREA CONSTRUIDA	330.0 M2	UBICACION	
AREA LIBRE	27,325.0 M2	LOCALID	PATAYPAMPA
AREA TOTAL	27,673.0 M2	DISTRITO	PATAYPAMPA
		PROV	GRAU
LEVANT	DISEÑO	DPTO	APURIMAC
Ing J.C.C		ESCALA	

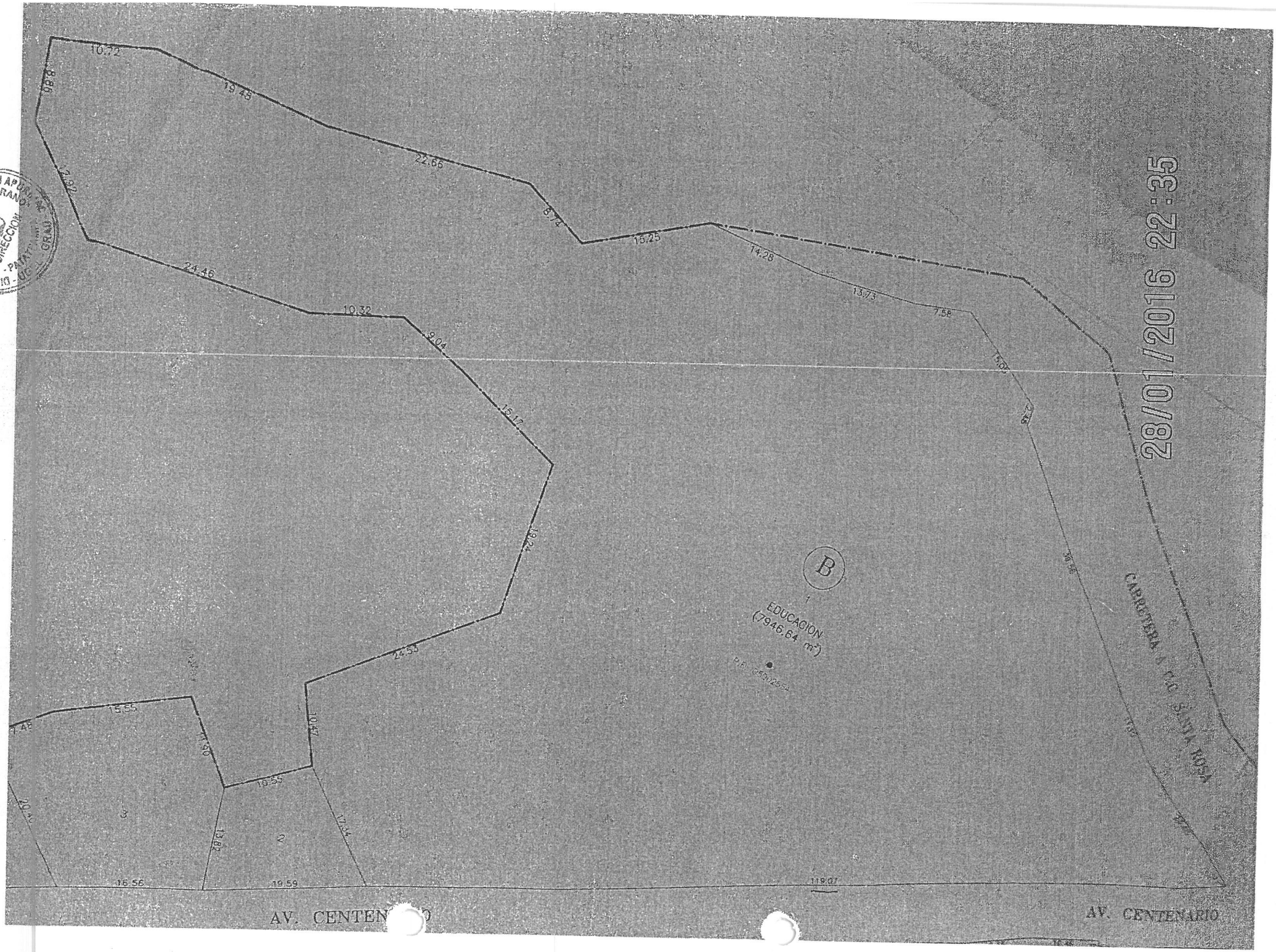
28/01/2016 22:35
B
1
EDUCACION
(7946.64 m²)
P.E. 6502654
CARRETERA A PO. SANTA ROSA
AV. CENTENARIO
AV. CENTENARIO
10.72
19.48
22.66
8.74
15.25
14.28
13.73
7.58
24.46
10.32
9.04
15.17
24.53
10.47
10.55
15.55
16.56
19.59
119.07